Z archiwum „J" cz. V
Białe plamy w Jaskini Czarnej

Tekst i zdjęcia: **Jakub Nowak**

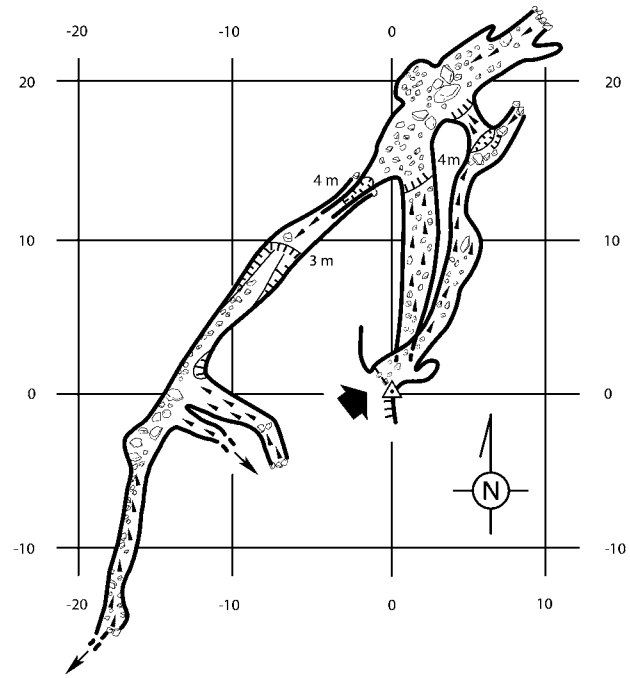

Zwiedzając Jaskinię Czarną, łatwo zapomnieć, że na jej długość w większości składają się ciągi boczne. Z szacowanej przez inwentaryzatorów długości 6,5 km ok. 450 m przypada na Partie III Komina, 1840 m – na Partie Tehuby, a ok. 930 m – na Partie Wawelskie. Niestety już pobieżny ogląd dokumentacji kartograficznej wskazuje, że jest ona równie niekompletna, jak znajomość historii eksploracji tej popularnej jaskini. Byłem jednak zaskoczony, gdy podczas jednej z wizyt stanąłem nad „nieistniejącą" studzienką. W czerwcu br. razem z Sylwią Gołosz-Romańską sprawdziłem te partie, a także położony poniżej Sali Francuskiej ciąg prożków i pochylni, o którym dowiedziałem się od Filipa Filara. Tydzień później razem z Mirosławem Pindlem zmierzyliśmy te zapomniane ciągi na łączną długość 200 m. Razem z odkryciami w rejonie Sali Bernarda (JASKINIE 61) dało to łączną długość ok. 6740 m.

Ciąg przed Salą Fracuską

Długość: 120 m
Deniwelacja: 30 m

Ciąg bierze początek za Prożkiem Rabka, zaraz pod następnym, czwórkowym prożkiem przed Salą Francuską. W tym miejscu w inwentarzu opisano większy korytarz: „W kierunku północno-wschodnim opada kamienisty korytarz, który po około 30 metrach kończy się ślepo. W swojej środkowej części korytarz ten połączony jest z kontynuacją ciągu głównego pionowym kominem". Między nim a prożkiem zaczyna się mniejszy korytarz dosyć stromo opadający nad ciasną studzienkę (P 6). Po zjechaniu nią stajemy w obszernym korytarzu o szerokości i wysokości do 4 m. Na północ, po 9 m korytarz zamyka zawalisko. Na południe, po kilku metrach korytarz przez 4-metrowy próg wznosi się kilkunastometrową pochylną zakończoną zawaliskiem pod ciągiem głównym. Przed progiem, po prawej znajduje się druga ciasna studzienka. Cztery metry niżej stajemy w następnym piętrze. Dalej rozszerzający się korytarz opada 3-metrowym progiem do obniżenia, za którym na wschód wznosi się 13-metrowy komin zakończony salką z zawaliskiem. Tuż za nim znajduje się drugi,

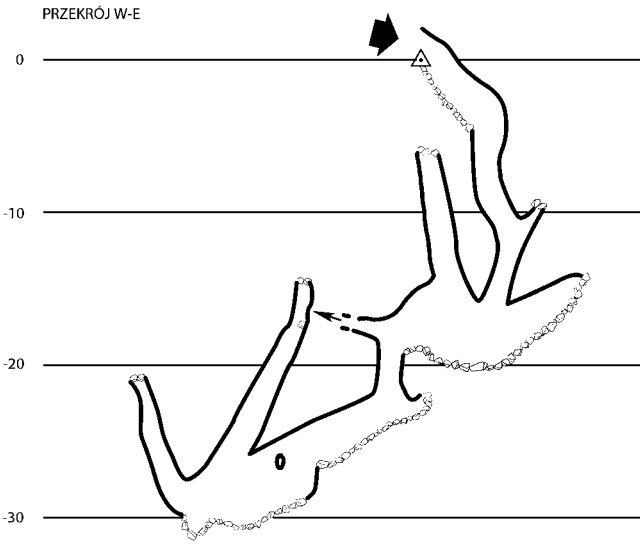

krótszy i ciaśniejszy komin równoległy. Idąc dalej korytarzem na południe, wchodzimy do szczelinowej pochylni o gruzowym dnie. Ciąg ten wznosi się i po kilkunastu metrach kończy w zawaliskowej salce.

Jest to dolne piętro ciągu głównego, powstałe na tym samym pęknięciu. Szata naciekowa występuje w całym ciągu, ale najbogatsza jest na najniższym poziomie. Tworzą ją grzybki naciekowe, mleko wapienne, polewy oraz niewielkie stalaktyty i stalagmity. Namulisko jest w większości gruzowe, miejscami zalegają duże bloki skalne. Przewiew jest nieznaczny. Okresowy ciek wodny występuje w 13-metrowym kominie. Resztki lin sizalowych wskazują, że ciąg ten był eksplorowany jeszcze w latach 60. XX w.

Pomiary: Jakub Nowak, Mirosław Pindel; 23.06.2012 r. ▷



Ciąg pod Salą Francuską

Długość: 80 m
Deniwelacja: 45 m

Ciąg bierze początek w najniższym miejscu Sali Francuskiej. Między blokami skalnymi schodzimy 3-metrowym prożkiem na dno piarżystej pochylni. Przechodzimy przez obniżenie z zaklinowaną wantą i stajemy nad 4-metrowym prożkiem. Pod nim schodzimy nad następny 5-metrowy prożek i dalej 20-metrową, obszerną pochylnią z ruchomym piargiem. Za nią zjeżdżamy kilkanaście metrów dnem skośnej szczeliny, na której powstał cały ciąg. Stajemy na dnie pochyłego korytarza. W górę prowadzi on do północnego krańca szczeliny, a w dół na południowy, przez płytę wchodzimy do kontynuacji szczeliny z zawaliskiem. W tej okolicy nastąpiło połączenie z Partiami nad Syfonem Tehuby. Szata naciekowa jest uboga, tworzą ją mleko i polewy. Na spągu zalegają gruz i duże bloki skalne, które stanowią spore zagrożenie. Przewiew jest nieznaczny. Opisywany ciąg został prawdopodobnie poznany później, być może w latach 70. XX w. Wcześniej najniższa część Sali Francuskiej była wykorzystywana jako latryna (ślady widoczne są do dzisiaj), co zapewne nie zachęcało do eksploracji. Filip Filar poinformował mnie, że ratownicy TOPR-u znają ten ciąg od dłuższego czasu, ale nie znają jego historii. Co ciekawe, Izabella Luty wykonała pomiary Partii Tehuby na przełomie lat 70. i 80. XX w. oraz uzupełniła je w 1995 r. i najwyraźniej nie wiedziała o ciągu prowadzącym do Sali Francuskiej. Dokumentacja tego ciągu zapewne nie istnieje, a historia jego odkrycia będzie trudna do ustalenia. Możliwe też, że odkrywcy samego połączenia z Tehubami (być może była to zupełnie inna ekipa) nie miała nawet tego świadomości, bo nastąpiło ono w nieprzyjemnym, szczelinowym zawalisku, które trzeba strawersować. Tak czy inaczej, w ten sposób powstała ciekawa pętla dająca możliwość trawersowania Partii Tehuby lub w ogóle dostęp do nich przy skrajnie dużym oblodzeniu wejścia prowadzącego tam z Sali Ewy.

Pomiary: Jakub Nowak, Mirosław Pindel; 23.06.2012 r. Dowiązanie tego ciągu do planu całej jaskini nie jest możliwe ze względu na dużą rozbieżność skrajnych punktów w tych ciągach. □

Literatura

Grodzicki J., Kondratowicz R., Kotarba S., Luty I., Recielski K., Zyzańska H. 1995. Jaskinia Czarna. [w:] Grodzicki J. (red.) 1995. Jaskinie Tatrzańskiego Parku Narodowego. Wielkie jaskinie Doliny Kościeliskiej. PTPNoZ – Warszawa. 101–127.

Kuryłowicz M. 2010. Nieudane „obejście" Colorado. Jaskinie 61:6.

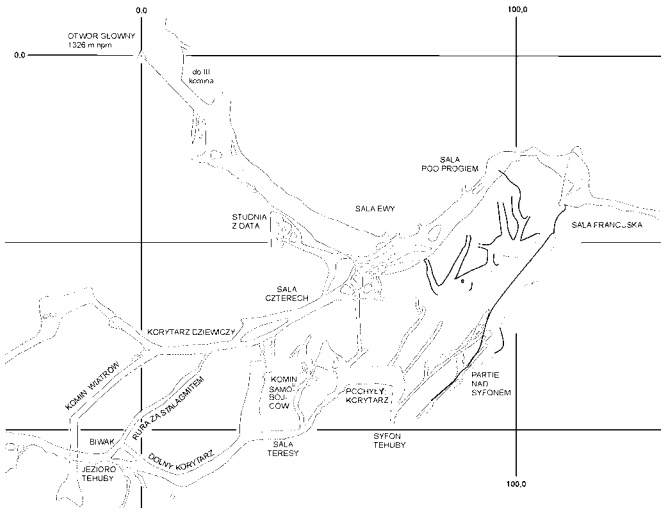
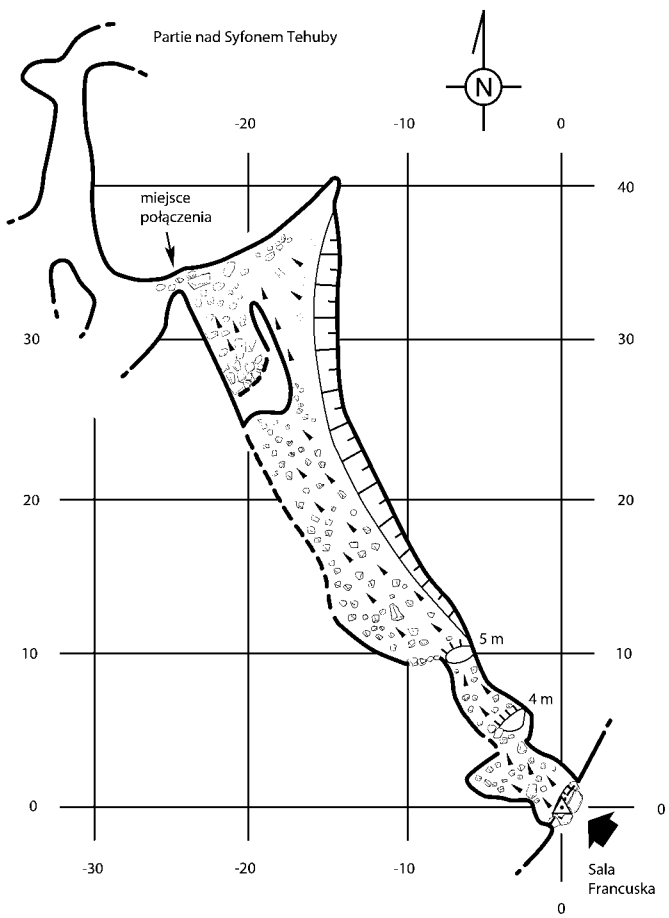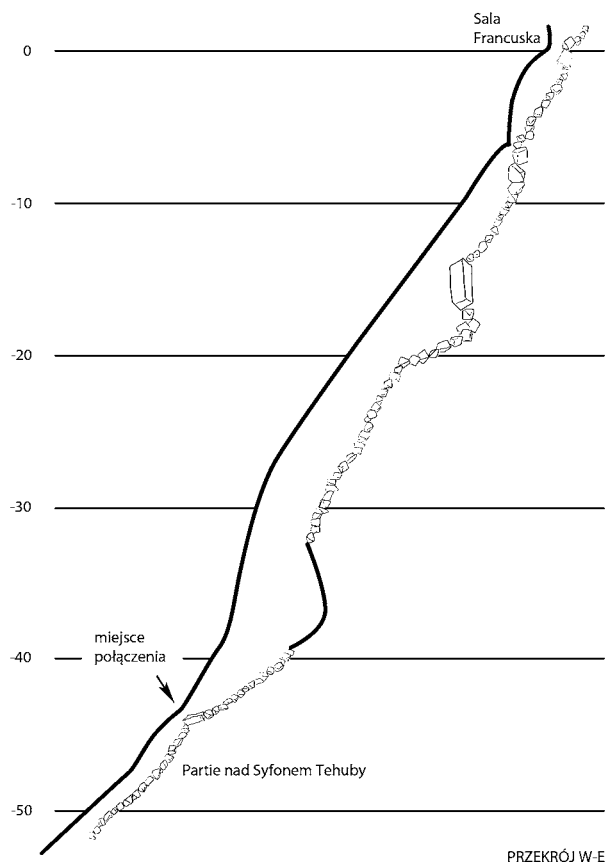
Jaskinia Czarna
przekrój zrzutowany na płaszczyznę W–E
wg Grodzicki i in.: 1995