Z archiwum „J" cz. VI

Jaskinia Czarna 50 lat później

Jakub Nowak

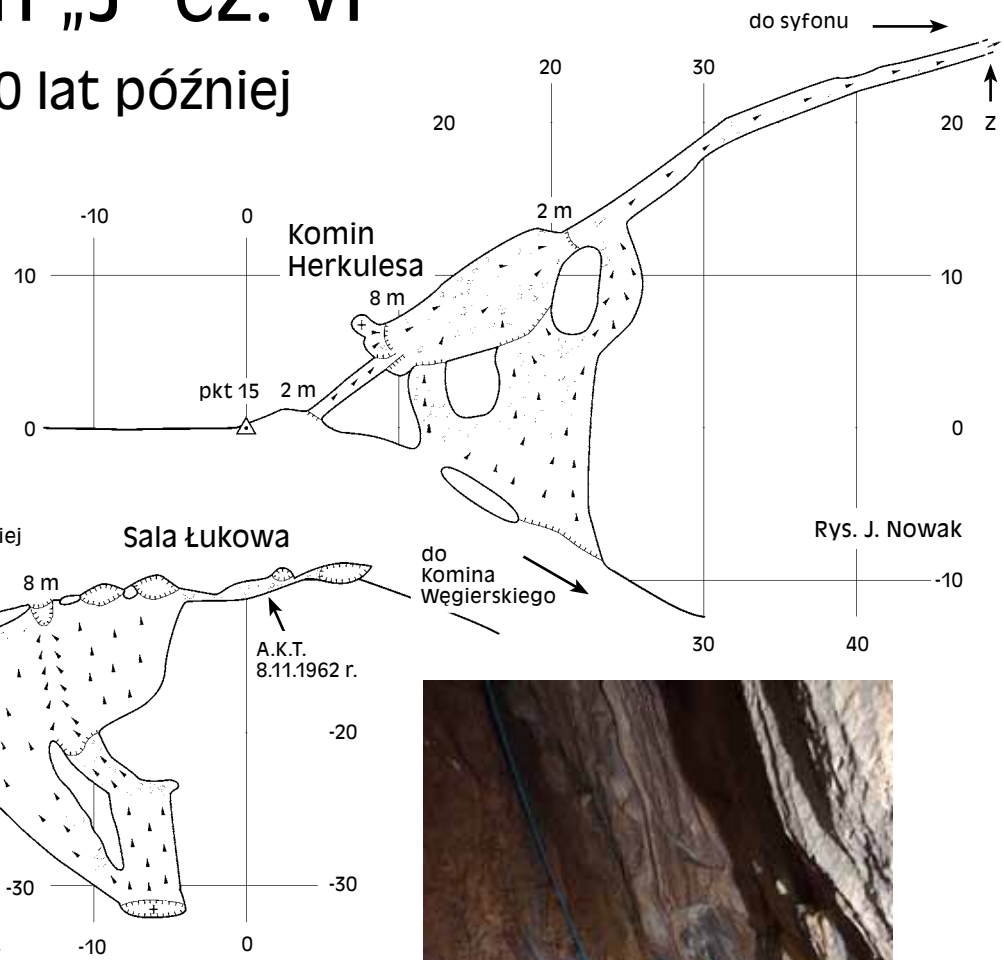

Dzięki Maciejowi Mieszkowskiemu udało się odtworzyć część historii odkryć, o których pisałem w JASKINIACH 67. Załącznik do e-maila od Macieja zawierał zdjęcia części tzw. *planu wrocławskiego*, z którego podobno korzystali twórcy inwentarza TPN. Plan powstał w latach 1961–63, czyli na początku eksploracji. Wynika z niego, wbrew temu co twierdziłem, że ciąg łączący Salę Francuską z Partiami Tehuby był znany już w latach 60. (na owym planie jest to zaznaczone jedynie schematycznie). Natomiast dalej nic nie wiadomo o historii eksploracji „ciągu przed Salą Francuską". Jednocześnie, nie rozstrzygając o poprawności językowej, należy wspomnieć o rozbieżnościach w nazewnictwie między planami z lat 60. i 90. XX w. Dotyczy to nazw: *Te**ch**uba – Partie Te**h**uby, Komin Wariatów – Komin Wiatrów, Komin Smoluchowskiego – Studnia Smoluchowskiego* (pierwsza podana wyżej wersja pochodzi z planu powstałego w latach 60., druga – 90.).

Kontynuowałem zwiedzanie kolejnych ciągów bocznych, dodatkowo zachęcony przez Macieja. Oprócz niżej podpisanego w pracach udział wzięli: Sylwia Gołosz-Romańska, Mirosław Pindel, Przemysław Styrna, Sebastian Styrna, Marcin Urban. W czasie kilku akcji spenetrowaliśmy rejon „Herkulesa" i Sali Łukowej. Efekty opisuję poniżej. Łączna długość domierzonych ciągów wynosi 200 m, zatem długość całej jaskini można szacować na ok. 6940 m.

Kominy nad Salą Łukową

Długość: 100 m
Deniwelacja: 60 m

Idąc z Sali Francuskiej, przechodzimy obniżenie stropu i wchodzimy do Sali Łukowej. Na pęknięciu w stropie sali widać kolejne okna prowadzące do obszernego komina. Mijamy pierwsze, największe z nich, i wspinamy się 8 m do następnego (III+). Wstecz, na SW wznosi się 5-metrowy korytarzyk obrywający się we wspomnianym pierwszym oknie. Wprost do góry wspinamy się wzdłuż rynny najłatwiejszą częścią szczeliny (III); 28 metrów wyżej stajemy na pochyłej, piarżystej półce. Wcześniej komin rozdziela się na dwie części za sprawą filara ciągnącego się przez ok. 30 m w górę. Z półki wspinamy się szczeliną (IV), która jest coraz ciaśniejsza i coraz bardziej stroma, a po 25 metrach staje się niedostępna. Najwyższy punkt znajduje się powyżej poziomu otworu głównego.

Wracamy do rozwidlenia nad drugim oknem. Stąd na NE trawersujemy stromą szczeliną (III–IV) nad trzecim i czwartym oknem, a następnie przez zaklinowane płyty wspinamy się do kontynuacji szczeliny. Tam tworzy ona wąski korytarzyk o wysokości do 2,5 m. Po kilku metrach obrywa się on studnią i piątym oknem, a po następnych dwóch – kolejną studnią i szóstym oknem w stropie ciągu głównego.

Nacieki w tym ciągu tworzą niewielkie stalagmity, grzybki, polewy i mleko wapienne. Na spągu zalega gruz. W kominie utrzymuje się cieplejsze powietrze (brak wyraźnego przewiewu). Okresowy ciek wodny spływa ze szczytu komina przez rynnę i drugie okno do Sali Łukowej, gdzie niknie w gruzie.

Ciąg został poznany przez członków Sekcji Grotołazów Akademickiego Klubu Turystycznego prawdopodobnie w całości w 1962 roku, a dokładnie w czasie wyprawy kierowanej przez Teresę Janasz (5–15 lutego). Wskazuje na to data „wykopcona" w rozszerzeniu korytarza między czwartym a piątym oknem (A.K.T. 8. II. 1962 r.) oraz napis AKT wykuty nad półką w połowie komina. Po poprzednikach pozostała również rozkładająca się lina sizalowa. Na planie wrocławskim szkicowo narysowany jest tylko trawers nad oknami, komin nie jest zaznaczony. W inwentarzu jaskiń TPN ciąg ten w całości pominięto i na planie, i w opisie, mimo że w historii eksploracji wspomniano o nim.

Pomiary: J. Nowak, M. Pindel, P. Styrna; 1.12.2012 r. i 9.12.2012 r. Ciąg pomiarowy został dowiązany do punktu nr 15 zaznaczonego na ścianie w ciągu głównym. ▷

△ *Wspinaczka nad Salą Łukową*
• *fot. J. Nowak*

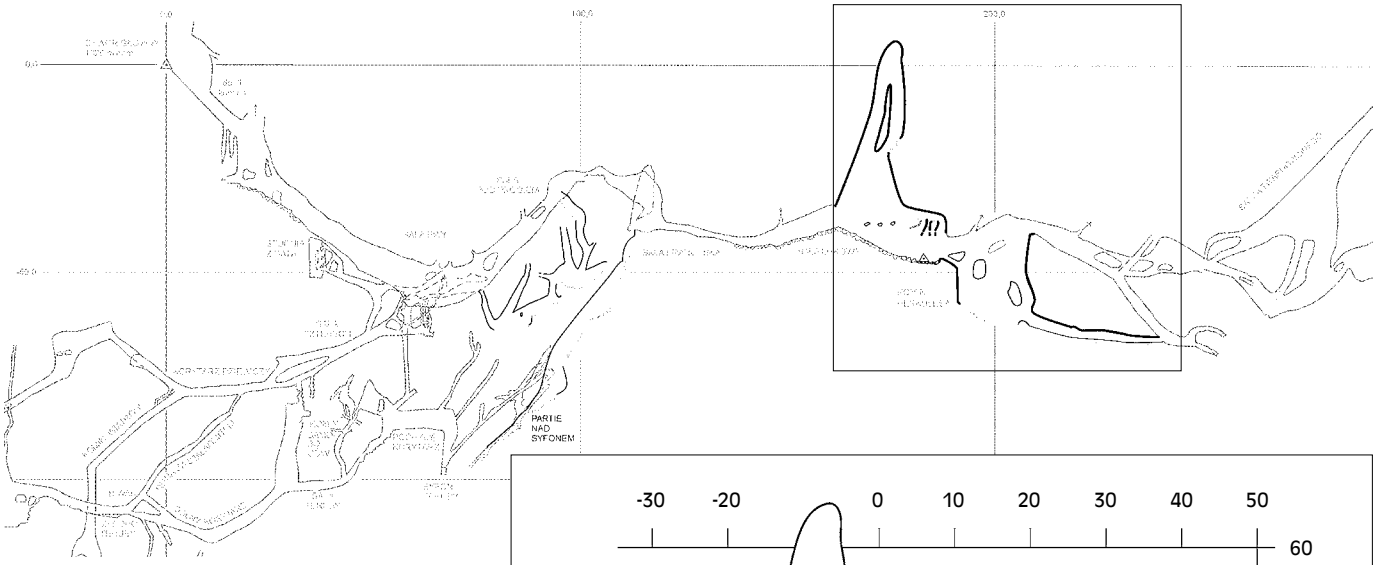

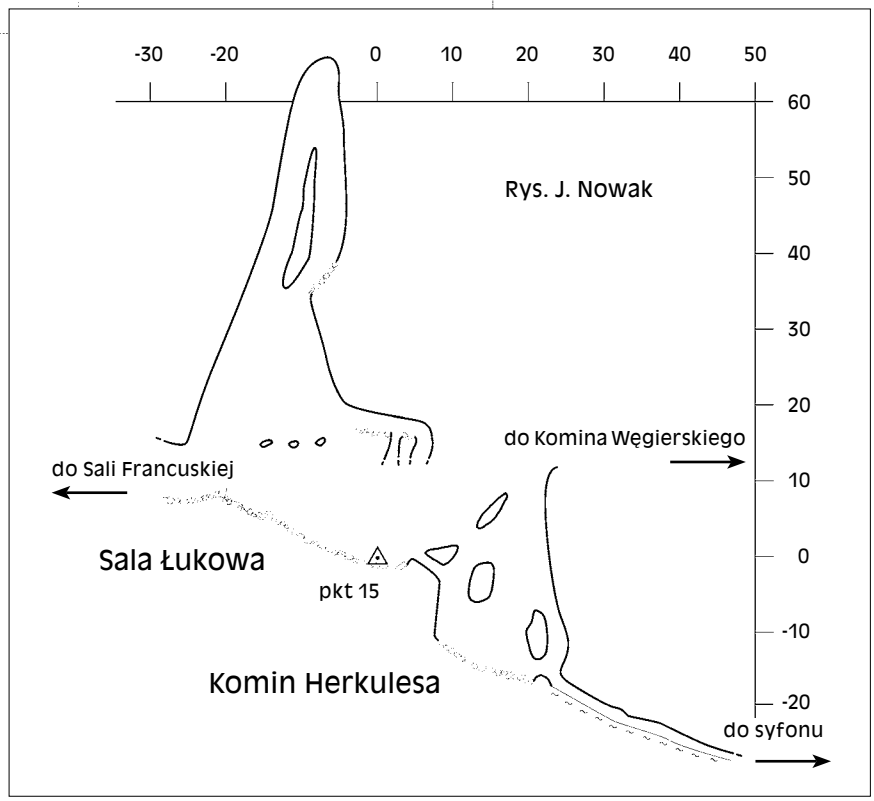

Jaskinia Czarna
(fragment)
przekrój zrzutowany na płaszczyznę W–E
wg Grodzicki i in.: 1995
Wyróżniono i dopasowano ciągi domierzone w 2012 r.

Do studni nad oknem piątym i szóstym nie zjeżdżano, stwierdzając jedynie ich połączenie z ciągiem głównym. Ze względu na zagrożenie „wiszącym" gruzowiskiem, nie sprawdzano odnogi komina za filarem.

Rysunki: J. Nowak

Komin Herkulesa

Długość: 100 m
Deniwelacja: 35 m

Z najniższej części Sali Łukowej (pkt 15) ciąg główny zakręca na SE i wznosi się, natomiast na NE prowadzi rura, do której dostajemy się przez dwumetrowy próg.

Po kilku metrach stajemy na mostku skalnym, który obrywa się 8-metrowym progiem z półką w jego połowie. Od północy wypada nad nią ślepy komin. Spod progu opada obszerna sala – wg planu wrocławskiego Komin Herkulesa. Sala ma wymiary 15×5 m i wysokość ok. 8 m. W jej południowym ograniczeniu otwiera się duże okno prowadzące do ciągu głównego. Z NE końca sali wspinamy się 2-metrowym progiem i stajemy na rozdrożu. Na wprost, w dół schodzimy prawie 30-metrowym, niskim korytarzem na rozmytej szczelinie. Na jego końcu znajduje się ciasny przełaz, za którym dochodzimy do syfonu. Wracamy do rozdroża. Stamtąd na S wspinamy się obszerną rurą. Po kilkunastu metrach stajemy w obszernej, połogiej szczelinie usłanej gruzem. Na NW obrywa się ona progiem ze wspomnianego okna w sali, natomiast w górę szczelina coraz stromiej wznosi się do dwóch okien prowadzących do ciągu głównego. Łatwiej jest się wspiąć do okna po prawej, które osiągamy po krótkim trawersie (II). Są to szczelinowe studnie, które bez asekuracji mija każdy grotołaz idący ciągiem głównym. W tym kontekście, trzymając się nomenklatury planu wrocławskiego, „trawers Herkulesa" – to jest właśnie to miejsce, a nie odcinek linowy nad pochylnią sprowadzającą do syfonu. Nacieki tworzą niewielkie stalagmity i stalaktyty, grzybki, polewy i mleko wapienne. Namulisko gruzowe, w korytarzu do syfonu – gliniaste. Przewiew w tym miejscu jest nieznaczny. Ciek wodny wypada z komina nad progiem i zanika w gruzie w sali.

Cały ciąg prawdopodobnie został poznany w 1961 lub 1962 roku. Na planie wrocławskim narysowana jest całość. W inwentarzu TPN na planie ciąg ten w całości pominięto, a w opisie wspomniano jedynie: „na styku lewej ściany ze spągiem obserwujemy na długości około 6 m szczelinę bardzo stromo opadającą, w dole łączącą się z partiami za Studnią Herkulesa". Wynika z tego, że twórca opisu tam nie był, a enigmatyczny opis połączenia był oparty na oglądzie planu wrocławskiego, stąd zapewne złe umiejscowienie i zmiana nazwy z „Komina Herkulesa" na „Studnię Herkulesa".

Pomiary: J. Nowak, S. Gołosz-Romańska, P. Styrna; 3.11.2012 r. Ciąg pomiarowy został dowiązany do punktu nr 15 zaznaczonego na ścianie w ciągu głównym.

Rysunki: J. Nowak

Przy okazji pomiarów z rejonu pkt 15 wyniesiono część śmieci pochodzących zapewne jeszcze z czasów eksploracji. □

Literatura

Grodzicki J., Kondratowicz R., Kotarba S., Luty I., Recielski K., Zyzańska H. 1995. Jaskinia Czarna. [w:] Grodzicki J. (red.) 1995. Jaskinie Tatrzańskiego Parku Narodowego. Wielkie jaskinie Doliny Kościeliskiej. PTPNoZ – Warszawa. 101–127.